Версия ПО ADS

ADS SE V4.0.0

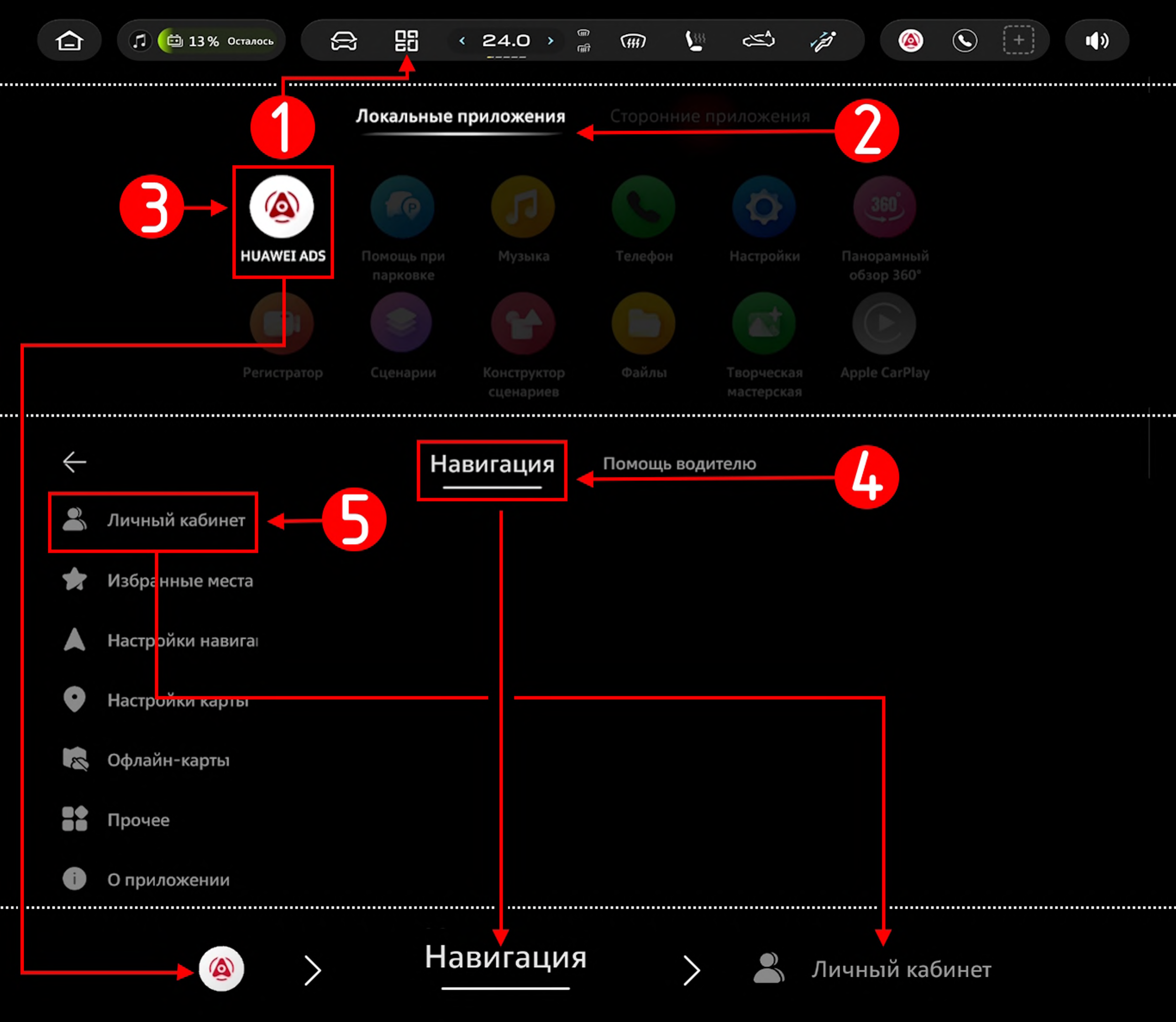
13 % Осталось
24.0
1
Локальные приложения
Сторонние приложения
2
3
HUAWEI ADS
Помощь при парковке
Музыка
Телефон
Настройки
Панорамный обзор 360°
Регистратор
Сценарии
Конструктор сценариев
Файлы
Творческая мастерская
Apple CarPlay
Навигация
Помощь водителю
4
Личный кабинет
5
Избранные места
Настройки навига
Настройки карты
Офлайн-карты
Прочее
О приложении
Навигация
Личный кабинет

Нажмите для входа в аккаунт Huawei

Мой автомобиль

Укажите номерной знак для объезда ограничений

ДОБАВИТЬ

Привязать аккаунт WeChat

Отправка сообщений с местоположением из чата WeChat на автомобиль

ДОБАВИТЬ

Привязать аккаунт Amap

После привязки история поиска, избранное и навигации, связанные с вашим аккаунтом Huawei, будут синхронизированы и сохранены.

ДОБАВИТЬ

Дом и работа

Дом

Нажмите для установки домашнего адреса

Работа

Нажмите для установки

Войдите в аккаунт Huawei для просмотра избранных мест

Предпочтения маршрута

ИНТЕЛЛЕКТУАЛЬНАЯ РЕКОМЕНДАЦИЯ

ИЗБЕГАТЬ ПРОБОК

БЕЗ АВТОМАГИСТРАЛЕЙ

ПРИОРИТЕТ АВТОМАГИСТР

МЕНЬШЕ ПплатНЫХ

САМЫЙ БЫСТРЫЙ

ПРИОРИТЕТ ГЛАВНЫХ

Объезд ограничений

При включении будет объезжать дороги с

Навигационные оповещения

Подробное оповещение	Краткое оповещение

Свободный круиз

Автоматический переход в режим круиза

Содержание оповещений при круизе

Если ничего не выбрано, оповещения при круизе отключены

Дорожная обстановка впереди

Оповещение о камерах

Предупреждения безопасности

Специальные возможности

Автоматическое изменение масштаба карты при навигации и круизе
Для оптимального отображения карты и обзора

Быстрая навигация
Быстрый запуск навигации к часто используемым местам

Рекомендации часто посещаемых мест
При включении будут автоматически предлагаться часто посещаемые места и быстрый запуск навигации

Несколько альтернативных маршрутов
При включении в навигации будут автоматически предлагаться альтернативные маршруты

Навигация > Настройки карты

Размер текста на карте

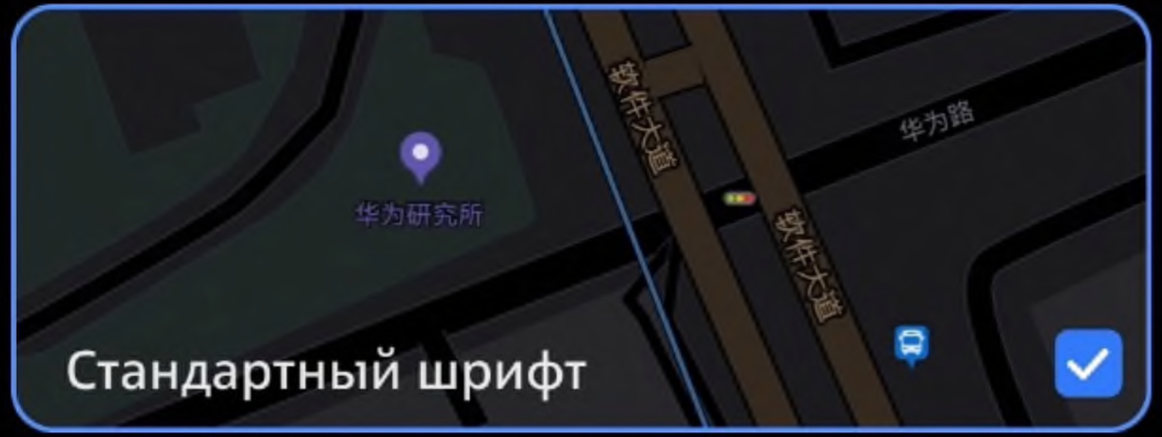

Отображение компаса на значке авто





Введите название города или первые буквы

Управление загрузками

ПРОСМОТР

Текущий город

基础功能包 · 30,9MB

ЗАГРУЗИТЬ

Базовый пакет функций

Необходимо для межд…

ЗАГРУЗИТЬ

Рекомендуемые ближайшие города 0,0KB ЗАГРУЗИ···

Город центрального подчинения 1,3GB ЗАГРУЗИ···

安徽省 527,4MB ЗАГРУЗИ···


Навигация
Прочее

Проверить обновления

Вопросы и предложения

Очистить кеш 0,64MB

Сбросить все настройки

Petal Maps

3.1.0.494

Телефон службы поддержки

951998

Лицензии открытого исходного кода

Пользовательское соглашение Petal Maps (автомобильная версия)

Условия использования AutoNavi и Политика конфиденциальности AutoNavi

UUID: [redacted]

互联网审图号: GS（2023）907号 | GS（2023）551号

ADAS审图号：GS（2025）4063号 | GS（2023）4320号 | GS（2024）5100号

苏ICP备17040376号-155A (https://beian.miit.gov.cn)

Все права защищены © 2026 Petal Maps

Помощь водителю > Продвинутый ассистент

Подтверждение смены полосы

Всегда | Никогда

Активность при смене полосы

Осторожный | Стандартный | Решительный

Смещение ограничения скорости

Фиксированное | Процентное

Смещение

+ 0 km/h

Целевая скорость = текущее ограничение + фиксированное смещение

Приоритет эффективности

При включении автомобиль интеллектуально реагирует на дорожную обстановку

Адаптивный круиз-контроль

При отключении адаптивный круиз-контроль не будет активироваться при деактивации круиза по полосе или н···

Помощь водителю > Ассистент парковки

Скорость парковки

Низкая | Средняя | Высокая

Предотвращение выезда из полосы

Выкл. | Предупреждение | Предупреждение + Коррекция

Тип оповещения

Звуковой сигнал | Вибрация | Звуковой сигнал + Вибрация

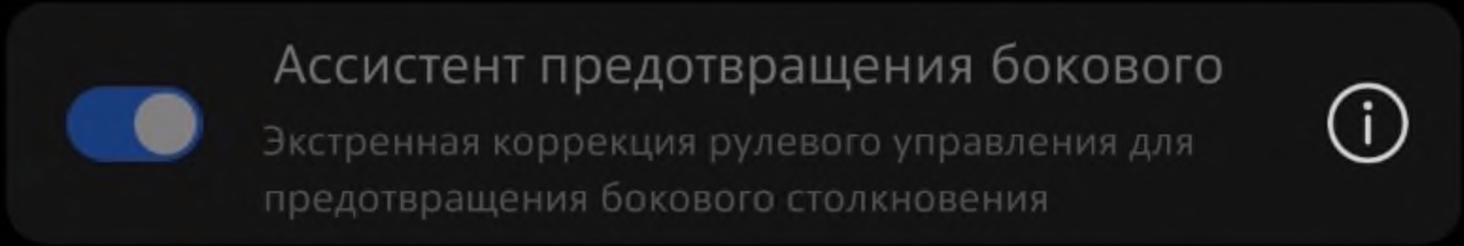
Ассистент предотвращения бокового
Экстренная коррекция рулевого управления для предотвращения бокового столкновения



Предупреждение о столкновении

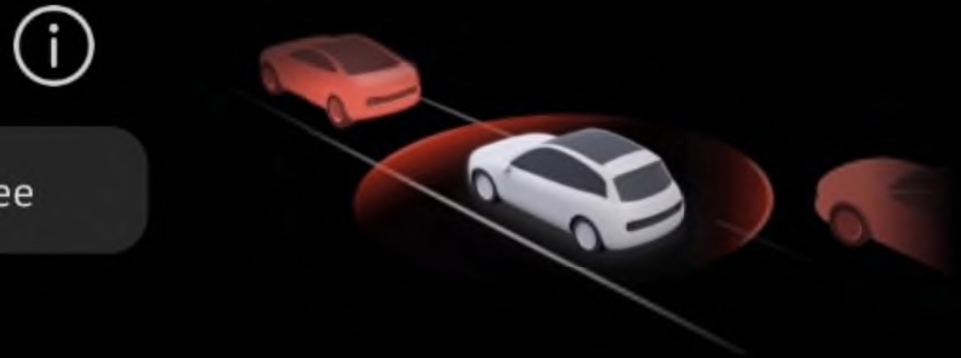

Выкл. | Позднее | Среднее | Раннее

Предупреждение о столкновении

Предупреждение о риске столкновения при переключении на D или R

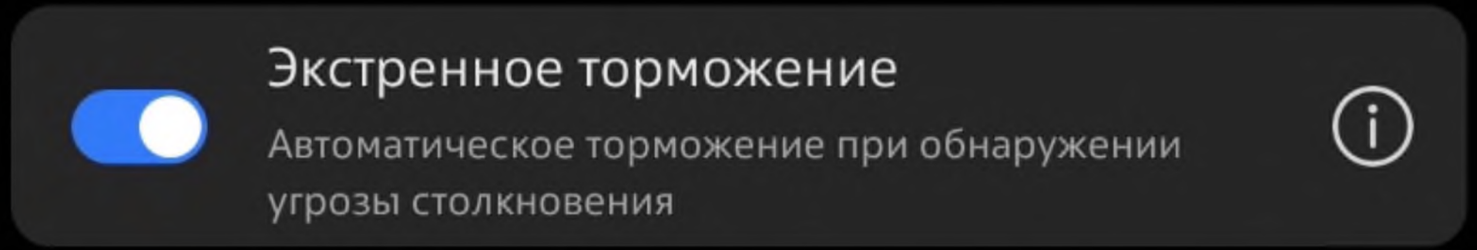
Экстренное торможение
Автоматическое торможение при обнаружении угрозы столкновения

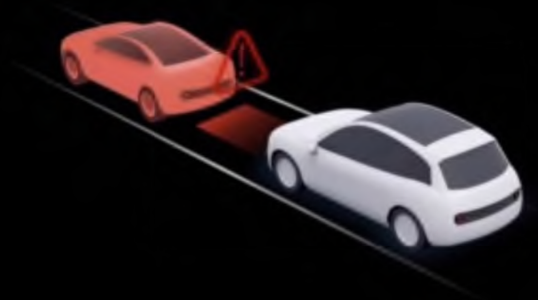

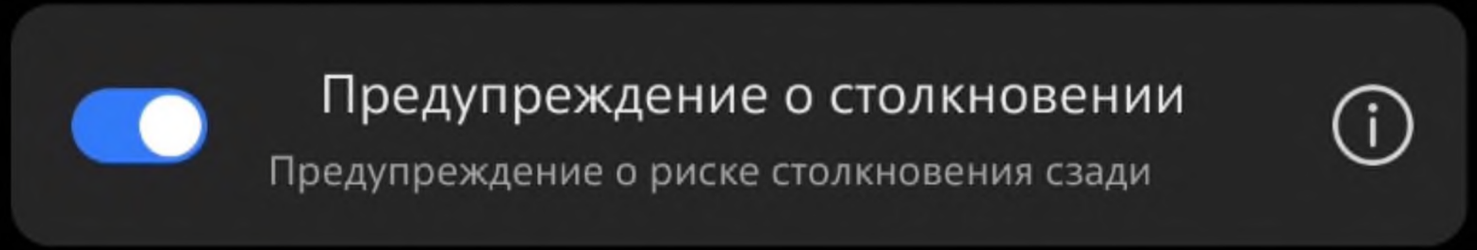
Предупреждение о столкновении
Предупреждение о риске столкновения сзади



Предотвращение

Ограничение ускорения при обнаружении препятствий спереди или сзади

Предупреждение о мёртвой зоне

Выкл. | Световой | Световой + Звуковой

Предупреждение при открытии

Предупреждение об опасности при открытии дверей

Предупреждение о скорости

Предупреждение при превышении установленного ограничения скорости

Распознавание светофоров

Подсказки для остановки и начала движения

Помощь водителю > 360 Круговой обзор

Открывать при переключении на R

Интеллектуальный ассистент парковки

Обзор 360°

Обзор на узкой дороге

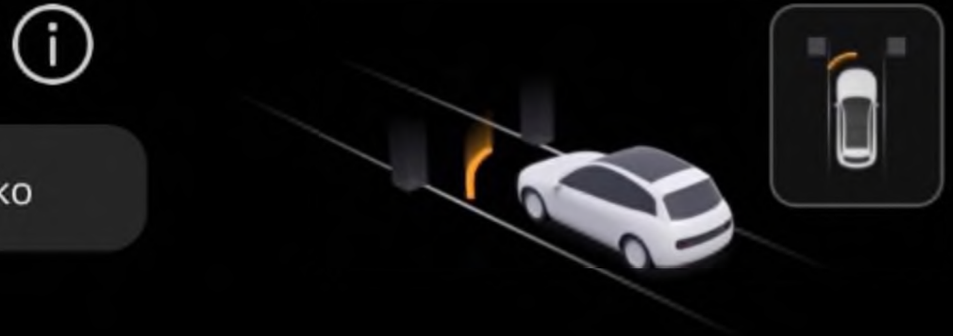

Выкл. | Близко | Средне | Далеко

Прозрачность автомобиля

Выкл. | Низкая | Высокая

Уведомления ADS

Краткий | Подробный

Индикаторы ADS

Включение внешних индикаторов ADS при активной системе

Калибровка ADS

Калибровка ADS

Повторная калибровка датчиков ADS

Помощь водителю > Тест безопасности

Отсканируйте через приложение для прохождения теста по безопасности ADS

Все функции ADS будут доступны только после прохождения всех тестов. Подробнее о функциях ADS см. в Руководстве водителя

РУКОВОДСТВО ВОДИТЕЛЯ

Загрузка...

Помощь водителю > Отчёт об использовании

Отчёт недоступен

Войдите в аккаунт владельца для просмотра

Помощь водителю > О программе

Версия ПО ADS

ADS SE V4.0.0

Заявление об открытом программном обеспечении

Заявление о конфиденциальности ADS

Список персональных данных, собираемых сторонними SDK

Petal Maps

Список собираемых персональных данных

Сведения о передаче персональных данных третьим лицам